Wydział Matematyki i Nauk Informacyjnych
POLITECHNIKA WARSZAWSKA

Podstawy Teorii Informacji

Laboratorium 2

Raport projektowy MiniInfo

MiniInfo - Raport 2

Autorzy

Goran Pangełow
Marcin Pawlak
Mikołaj Pesta
Ignacy Dręźek
Iga Oleksiewicz
Maks Młynarczyk

21 marca 2026

Spis treści

1 Sprostowanie Raportu 1 i redefinicja celów badawczych 2
1.1 Analiza Raportu 1 2
1.2 Nowa koncepcja 2
1.3 Wkład Raportu 1 w rozwój nowego projektu 3

2 Charakterystyka problemu i analiza potrzeb użytkownika (Pragmatyka) 4
2.1 Kontekst logistyczny i geneza projektu „MINI Info” 4
2.2 Definicja celu i funkcja „Inteligentnej Rekomendacji” . . . 4
2.3 Parametryzacja zasobów i logika progowa 4
2.4 Wyzwanie techniczne: Precyzyjna detekcja obecności a zgodność z RODO 5

3 Modelowanie i reprezentacja informacji (Syntaktyka i Semantyka) 7
3.1 Poziom syntaktyczny: Zbieranie surowych danych 7
3.2 Jak często "pytać"czujniki? (Twierdzenie Nyquista w praktyce) 8
3.3 Poziom semantyczny: Interpretacja i sens informacji 9
3.4 Struktury wiedzy: Taksonomia stanów pokoju 10
3.5 Ile faktycznie "wiedzy"daje system? (Entropia Shannona) . 11
3.6 Architektura przesyłu danych 12
3.7 Podsumowanie przepływu informacji w architekturze systemu 13

4 Analiza alternatywnych metod akwizycji i wybór technologii 14
4.1 Analiza alternatywnych metod akwizycji (State-of-the-art) 14
4.2 Uzasadnienie wyboru technologii (Synteza wniosków) . . . 15
4.3 Implikacje pragmatyczne dla użytkownika końcowego . . . 16

5 Metryki efektywności i optymalizacja przesyłu (Kompresja i Jakość) 16
5.1 Porównanie podejść: kamery kontra czujniki obecności . . 16
5.2 Granularność danych wyjściowych i kryteria jakości informacji 18
5.3 Forma przesyłu danych i ich analiza 19

1 Sprostowanie Raportu 1 i redefinicja celów badawczych

1.1 Analiza Raportu 1

W związku z konstruktywną krytyką i niezwykle cennymi uwagami uzyskanymi po ocenie pierwszego raportu, nasz zespół projektowy po głębokiej ewaluacji naszych dotychczasowych prac podjął decyzje o całkowitej zmianie naszej koncepcji, zachowując cel jakim jest ułatwienie codziennego życia studentów na naszym wydziale. Analiza uwag Profesora doprowadziła nas do wniosku, że pierwotne założenia projektu – oparte na problemach nawigacyjnych, poszukiwaniu sal czy wektoryzacji planów ewakuacyjnych – choć interesujące z punktu widzenia architektonicznego i algorytmicznego, nie są możliwe do pełnego zrealizowania i wyczerpania tematów przewidzianych na PTI. Skupienie się na geometrii gmachu sprawiło, że w Raporcie 1 pominęliśmy kluczowe aspekty tego zadania czyli dynamikę przepływu danych, ich wiarygodność i pełną analizę nadmiarowości. Zgadzamy się z opinią, że problem odnajdywania sal jest barierą chwilową, z którą przeciętny student radzi sobie w pierwszych tygodniach nauki, a analiza dylematu „schody czy winda” posiada zbyt małą skalowalność, by oprzeć na niej złożony system informacyjny. Biorąc pod uwagę sugestie, by poszukać problemów bliższych codziennym aktywnościom społeczności akademickiej oraz skupić się na unikatowości naszego wydziału, podjęliśmy decyzję o całkowitej redefinicji tematu badawczego. W niniejszym, drugim etapie projektu, przenosimy punkt ciężkości ze środowiska statycznego na w pełni dynamiczne. Naszym nowym obszarem badawczym staje się modelowanie, ekstrakcja i optymalizacja przepływu informacji o dostępności miejsc użytku rekreacyjnego, na przykładzie wydziałowych pomieszczeń socjalnych i stref relaksu.

1.2 Nowa koncepcja

Wybór tego zagadnienia stanowi bezpośrednią odpowiedź na realne potrzeby studentów. Wydział MiNI, charakteryzujący się wysokim natężeniem ruchu w przerwach między blokami zajęciowymi, regularnie boryka się z problemem lokalnego przeludnienia stref wypoczynkowych. Z punktu widzenia studenta, decyzja o udaniu się np. do pokoju cichej nauki, które znajdują się na 4 piętrze, jest często bardzo niepewna i obarczona wysokim prawdopodobieństwem tzw. pustego przebiegu. Zaistnienie takiej sytuacji, czyli wędrówki do pomieszczenia, w którym brakuje wolnych miejsc siedzących, generuje stratę czasu, energii i frustrację. Zjawisko to możemy

traktować jako klasyczny problem deficytu informacyjnego. W takim ujęciu, dostarczona w odpowiednim czasie i formie informacja o aktualnym obłożeniu pomieszczenia nabiera ogromnej wartości pragmatycznej. W niniejszym raporcie, zgodnie z sugestiami Profesora, przyjmujemy podejście dedukcyjne – od ogółu do szczegółu. Zgodnie z założeniami ćwiczenia 2 będziemy traktować badane strefy jako źródła sygnału, a studentów jako jego odbiorców i dążymy do stworzenia optymalnego modelu redukcji niepewności. W poniższych rozdziałach dokonujemy rygorystycznego przeglądu literatury i istniejących na rynku rozwiązań z zakresu systemów Smart Building i Occupancy Sensing. Następnie analizujemy pozyskiwane dane informacyjne na trzech poziomach, to jest syntaktycznym, semantycznym i pragmatycznym oraz badamy możliwości ich kompresji w taki sposób, aby ewentualny efekt końcowy (np. ekrany informacyjne na korytarzach wydziału) dostarczał jak najwięcej informacji w przejrzysty sposób.

1.3 Wkład Raportu 1 w rozwój nowego projektu

Całkowita zmiana koncepcji, już po zakończeniu etapu pierwszego, pociąga za sobą jednak pewne problemy. Brak zgromadzonych pierwszych danych i obserwacji na nowy temat wstrzymywałby nas od kolejnych kroków. W związku z tym postanowiliśmy rozpocząć wszystko od zera i dla dalszych badań przeprowadziliśmy ponownie akwizycje i analizę próbkowania danych oraz weryfikacje ich jakości. Będą one wykorzystywane w niniejszym, jaki i przyszłych raportach, jednak stosując się do zasad klarowanie postawionych przez Profesora w trakcie trwania laboratoriów, nie ma możliwości ponownego napisania naszego poprzedniego sprawozdania, więc postanowiliśmy, że nie będziemy ich jawnie przedstawiać. Pomimo to poprzedni raport wniósł wiele kluczowych spostrzeżeń do naszego projektu i ukazał wady naszego podejścia do rozwiązywania zawiłych zagadnień. Najważniejsze wnioski jakie udało nam się wyciągnąć to przede wszystkim problem niejasno postawionych celów i zbytnie skupienie się na wzniosłych, ale nie możliwych do zrealizowania celach. Dodatkowo w trakcie zbierania danych i przeprowadzania eksperymentu udało nam się zdobyć cenne doświadczenie, które znacząco wpływa na jakość naszych przyszłych prac. W związku z wyżej wymienionymi, pomimo fiaska naszego pierwotnego pomysłu, raport 1 ma kluczowy wkład w dalszy rozwój naszych badań i był on nieocenioną nauką, której efekty będą jasno widoczne w trakcie trwania dalszych prac na PTI.

2 Charakterystyka problemu i analiza potrzeb użytkownika (Pragmatyka)

2.1 Kontekst logistyczny i geneza projektu „MINI Info”

Geneza systemu „MINI Info” jest ściśle uwarunkowana specyfiką architektoniczną gmachu Wydziału Matematyki i Nauk Informacyjnych. Wertykalny układ budynku oraz rozproszenie dedykowanych stref rekreacyjnych i naukowych na różnych kondygnacjach stanowią istotną barierę w procesie efektywnego zarządzania zasobami przestrzennymi. Dotychczasowy model eksploatacji infrastruktury opierał się na paradygmacie pasywnym, w którym przepływ osób nie był wspierany przez żadną formę dynamicznej warstwy informacyjnej. Wyzwanie logistyczne polega zatem na braku centralnego mechanizmu monitorowania stanu zajętości w czasie rzeczywistym. Projekt wyrasta z potrzeby implementacji inteligentnej infrastruktury, która przekształca izolowane pomieszczenia w aktywne źródła danych (ang. *data points*), zintegrowane w ramach scentralizowanego systemu wizualizacji dostępnego w głównym węźle komunikacyjnym wydziału.

2.2 Definicja celu i funkcja „Inteligentnej Rekomendacji”

Głównym celem systemu jest redukcja „kosztu dotarcia” do wolnego miejsca pracy lub odpoczynku. W zaproponowanym modelu system nie tylko pasywnie informuje o zajętości, ale pełni również funkcję aktywnego asystenta – sugeruje alternatywne lokalizacje. Jeśli wybrana przez studenta sala wykazuje wysoki stopień obłożenia, interfejs (ekran w lobby) automatycznie wskazuje najbliższą wolną przestrzeń o podobnym przeznaczeniu. Przykładowo, w sytuacji przepełnienia pokoju JetBrains, system wyświetli komunikat: „Brak miejsc w JetBrains. Sprawdź Laboratorium (piętro 1) – dostępność: Wysoka”.

2.3 Parametryzacja zasobów i logika progowa

Dla potrzeb systemu zdefiniowano bazę monitorowanych pomieszczeń wraz z ich nominalną pojemnością miejsc siedzących (C_{max}). Na tej podstawie algorytm wylicza stany obłożenia:

- Noga (Biuro WRS): ∼20 osób (przestrzeń integracyjna i biurowa)

- Pokój JetBrains: ∼25 osób (strefa warsztatowa i pracy grupowej)
- Laboratorium komputerowe: ∼15 osób (stanowiska do pracy własnej)
- Salki Nauki (3 obiekty): średnio ∼10 osób/salka (pokoje cichej pracy)

Logika interpretacji opiera się na priorytetyzacji komfortu. Przyjęto, że dla studenta kluczowa jest informacja o dostępnym miejscu siedzącym. Stany informacyjne prezentowane w lobby zmieniają się dynamicznie w zależności od obłożenia, a dodatkowo system posiada odrębny stan techniczny:

- 0-50% (Wolne / Dużo miejsc): pełna dostępność.
- 51-80% (Umiarkowany ruch): możliwość znalezienia pojedynczych wolnych miejsc.
- $> 80\%$ i $< 100\%$ (Prawie pełny): krytyczny poziom zajętości; aktywacja systemu rekomendacji alternatywnych sal.
- 100% (Pełny): komunikat o całkowitym braku miejsc.
- Sprzątanie (tryb techniczny): stan nadrzędny aktywowany przez obsługę; sala jest czasowo wyłączona z rekomendacji niezależnie od obłożenia.

2.4 Wyzwanie techniczne: Precyzyjna detekcja obecności a zgodność z RODO

Podstawowym problemem inżynieryjnym w projekcie jest bezbłędne odróżnienie osoby siedzącej (często w bezruchu, np. podczas czytania lub programowania) od pustego pomieszczenia, przy jednoczesnym rygorystycznym zachowaniu prywatności. Instalacja tradycyjnego monitoringu wizyjnego (CCTV) naruszałaby przepisy RODO i wywołała uzasadniony opór społeczności studenckiej wobec „inwigilacji” w strefach relaksu. Z kolei standardowe, tanie czujniki ruchu (PIR), powszechnie stosowane w systemach oświetlenia, rejestrują jedynie wyraźne przemieszczanie się – student siedzący nieruchomo przy laptopie staje się dla nich „niewidzialny”, co prowadziłoby do drastycznych przekłamań w systemie (tzw. zjawisko false negatives).

Zgodnie z zasadą Privacy by Design, projekt „MINI Info” zakłada wykorzystanie wyspecjalizowanych sensorów obecności nowej generacji, operujących na poziomie sprzętowej anonimizacji danych:

- **Radary fal milimetrowych (mmWave):** Technologia ta wykorzystuje wysokoczęstotliwościowe fale radiowe do mapowania przestrzeni. W przeciwieństwie do czujników PIR, sensory mmWave są w stanie wykryć mikroruchy, takie jak unoszenie się klatki piersiowej podczas oddychania czy bicie serca. Pozwala to na nieprzerwane monitorowanie obecności osób pracujących w całkowitym bezruchu, nie zbierając przy tym żadnych danych wizualnych.

- **System kontroli wejść RFID/NFC:** Czytniki legitymacji przy wejściach do stref pozwalają rejestrować strumień wejść i wyjść bez przetwarzania danych biometrycznych, co utrzymuje pełną zgodność z RODO i upraszcza audyt procesu.

W procesie projektowym rozważaliśmy również niskorozdzielcze matryce termiczne (np. Grid-Eye), ponieważ zapewniają one anonimowość i dobrą detekcję źródeł ciepła. Ostatecznie zrezygnowaliśmy jednak z ich wdrożenia na rzecz toru mmWave + RFID/NFC. Decyzję tę podjęliśmy z powodów pragmatycznych: niższej złożoności integracji z istniejącą infrastrukturą wejściową wydziału, mniejszych kosztów skalowania na wiele pomieszczeń oraz prostszej kalibracji i utrzymania eksploatacyjnego. W praktyce połączenie radaru obecności (detekcja realnej obecności także w bezruchu) z kontrolą wejść (kontekst zdarzeń drzwiowych) daje wysoką wiarygodność semantyczną danych wejściowych, zapewniając stabilne działanie systemu rekomendacji przy całkowitym braku ryzyka prawnego i etycznego związanego z przetwarzaniem danych osobowych.

Kluczowym wyzwaniem w rozwoju naszego zintegrowanego systemu wizualnego na Wydziale MiNI jest nie tylko wyznaczanie badanych wcześniej tras, ale przede wszystkim dostarczanie wiedzy na żywo o dostępności poszczególnych stref (np. *Pokój cichej nauki*, *Strefa Jet Brains*) bezpośrednio na wielkoformatowe ekrany w lobby. Aby było to możliwe, system musi nieustannie dokonywać zamiany fizycznego świata rzeczywistego na użyteczną postać cyfrową. Realizujemy to dzieląc zjawisko informacji na dwa zasadnicze poziomy: syntaktyczny (zbieranie struktury sygnałów) oraz semantyczny (nadawanie im ostatecznego znaczenia).

3 Modelowanie i reprezentacja informacji (Syntaktyka i Semantyka)

3.1 Poziom syntaktyczny: Zbieranie surowych danych

Na poziomie syntaktycznym system nie rozumie kontekstu zdarzeń na wydziale – zajmuje się jedynie automatyczną rejestracją surowej formy sygnałów fizycznych. Z uwagi na restrykcyjne normy prywatności i przepisy o ochronie danych (RODO), w projekcie całkowicie odrzuciliśmy możliwość korzystania z kamer wideo oraz jakichkolwiek mikrofonów. Podstawą naszego systemu stały się w pełni zanonimizowane urządzenia pomiarowe. Zbieramy następujące typy strumieni danych:

- **Czujniki obecności (sieć ZigBee[1]):** Gotowe radary milimetrowe (mmWave) podpięte pod sufity naszych sal. Zamiast tworzyć skomplikowaną obróbkę samych fal radiowych na backendzie, zrzucamy pracę na wbudowane oprogramowanie radaru. Otrzymujemy z niego po prostu surową liczbę typu `integer` (całkowitą), która mówi wprost: "widzę w tej sali fizycznie X osób".

- **System kontroli wejść na legitymacje (RFID/NFC):** Klasyczne czytniki zbliżeniowe montowane przed wejściem do określonych stref wydziału (takich jak *Pokój cichej nauki*). Każde odbicie fizycznej legitymacji generuje po prostu standardowy strumień systemowych zapytań dodających/odejmujących studenta z tablicy w bazie danych.

Z perspektywy prawa oświatowego i braku konieczności instalowania kamer – układ ten sprawdza się doskonale. Jednakże dla końcowego odbiorcy – czyli studenta w holu – goła liczba logowań z czytników czy surowe zera z ZigBee to na ten moment bezwartościowy szum (fizyczna syntaktyka). Wyświetlenie takich surowych i nieprzetworzonych porcji zmiennych na wielkich ekranach byłoby dla studentów po prostu brzydkie i stanowczo niezrozumiałe.

[1] ZigBee to popularny i wysoce energooszczędny standard łączności bezprzewodowej, powszechnie stosowany w branży Smart Home. Pozwala on łatwo i bezpiecznie połączyć wszystkie sensory na piętrze w jedną, wspólną i stabilną sieć komunikacyjną.

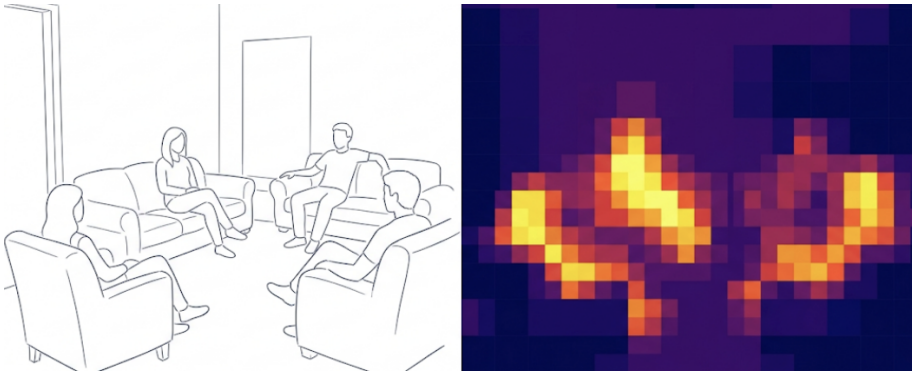

Rysunek 1: Koncepcyjny schemat topologii przestrzennej systemu. Skanowanie wnętrza za pomocą radaru (weryfikacja obecności statycznej) połączone z punktowym czytnikiem RFID w świetle drzwi.

3.2 Jak często "pytać"czujniki? (Twierdzenie Nyquista w praktyce)

W tym miejscu pojawia się jednak pewien twardy problem fizyczny: jak często nasze radary ZigBee i czytniki powinny „pytać” pokój o to, co się w nim dzieje? Tutaj na białym koniu wjeżdża słynne twierdzenie Nyquista-Shannona z wykładów. Żeby nasz serwer nie zwariował od nadmiaru danych i żebyśmy poprawnie odwzorowali to, co faktycznie dzieje się w pokoju (czyli uniknęli tzw. aliasingu), musimy dobrać idealny interwał próbkowania.

Gdybyśmy pobierali odczyt z radaru co 1 sekundę, zapchalibyśmy naszą sieć bezprzewodową gigantyczną ilością bezużytecznego szumu (nadmiarowość). Przecież studenci nie teleportują się z miejsc co sekundę! Z kolei sprawdzanie sali raz na 30 minut sprawi, że przegapimy momenty, kiedy ktoś wszedł, zjadł kanapkę i wyszedł. Z naszych pomiarów wynika, że średni czas rotacji na jednym krześle to około 15 minut. Dlatego na naszym serwerze na sztywno ustawiliśmy czas próbkowania (oznaczmy go jako T_s) na okrągłe 60 sekund. To w zupełności wystarczy, żeby wyłapać każdego nowego bywalca i świetnie odfiltrować szum (np. kogoś, kto tylko przeszedł przez pokój, żeby otworzyć okno).

Rysunek 2: Nasze podejście do próbkowania. Czerwone kwadraty pokazują momenty, w których system ściąga dane z sieci ZigBee, fajnie odzwierciedlając ciągłą rzeczywistość bez zapychania łącza.

3.3 Poziom semantyczny: Interpretacja i sens informacji

Aby odciążyć odbiorcę z nadmiarowości i dostarczyć wartość, dane muszą przejść cyfrową transformację na poziom semantyczny. Tu nasz autorski algorytm łączy i przetwarza surowe ciągi w konkretną wiedzę, dokonując dogłębnej interpretacji w pełni uwzględniającej anonimowość.

W naszym projekcie stawiamy na bardzo proste, programistyczne połączenie odczytów z obu urządzeń. Na poziomie semantycznym, zadaniem naszego oprogramowania jest po prostu zestawienie ze sobą surowych liczb i wywnioskowanie z nich jednego, pewnego wyniku dla konkretnej sali.

Działa to w naszej logice następująco: radar podwieszony nad małym pokojem do nauki (o pojemności 6 krzeseł) przesyła nam na serwer informację po API, że widzi fizycznie 4 osoby. Z kolei z bazy czytnika kart wynika, że wejście "odbiły"tylko 3 osoby. Nasz algorytm zawsze bezpiecznie wybiera większą wartość z tych dwóch źródeł, żeby się ubezpieczyć przed błędem sprzętowym (w tym przypadku zakładamy, że jeden student najzwyczajniej wszedł za kolegą bez przykładania własnej legitymacji do drzwi). Radar mądrze doliczył nam więc "brakującego"człowieka.

Mając wiarygodną wartość, system musi nadać jej jeszcze proste znaczenie (czyli przejść do warstwy semantycznej w 100%). Skrypt analizuje, że skoro sala ma wpisany stały limit 6 wolnych miejsc, to oprogramowanie w mgnieniu oka redukuje całą tę skomplikowaną dedukcję do czytelnego, graficznego komunikatu. Na wielkim ekranie w lobby zapala się prosty napis: **„Zajętość strefy: 4/6 miejsc”**.

Z perspektywy teorii i inżynierii danych określilibyśmy to klasycznym przeskokiem wymiarowości. Za kulisami ukrywamy zapytania do bazy języka SQL, wyliczany ruch milimetrowy Zigbee z opóźnieniami sieciowymi, a docelowo serwujemy studentowi na dole jasny wynik ułamkowy 4/6. Rzut oka na taki czysty kafel w systemie i nasz statystyczny odbiorca w sekundę podejmie decyzję, co robi dalej bez marnowania przerw między zajęciami na daremtne wycieczki po uczelni.

3.4 Struktury wiedzy: Taksonomia stanów pokoju

Żeby wyliczone obłożenie ułamkowe wyświetlało się w sensowny i szybki sposób dla studentów, ujednoliciliśmy podział stanów z progami z sekcji 2.3 i rozszerzyliśmy go o unikalny tryb techniczny. Aplikacja na serwerze przydziela je u dołu ekranów automatycznie, dając na mapie odpowiedni kolor kafelka:

1. **WOLNE / DUŻO MIEJSC (Zielony, 0-50%):** W sali dostępna jest wyraźna liczba wolnych miejsc. Status ten odpowiada pełnej lub wysokiej dostępności i zachęca do wejścia bez ryzyka „pustego przebiegu”.

2. **UMIARKOWANY RUCH (Żółty, 51-80%):** W pomieszczeniu trwa normalny ruch i nadal można znaleźć pojedyncze wolne miejsca, ale komfort wyboru jest mniejszy niż w strefie zielonej.

3. **PRAWIE PEŁNY (Pomarańczowy, >80% i <100%):** Poziom zajętości jest krytyczny. System zaczyna aktywnie promować alternatywne lokalizacje, aby ograniczyć niepotrzebne przejścia studentów.

4. **PEŁNY (Czerwony, 100%):** Brak wolnych miejsc siedzących. Sala jest oznaczana jako chwilowo niedostępna i pojawia się komunikat o rekomendowanej alternatywie.

5. **SPRZĄTANIE (Szary, tryb techniczny):** Mechanizm twardego serwisu o najwyższych uprawnieniach systemowych w hierarchii. Gdy pracownik techniczny odbija na czytniku swoją autoryzacyjną Kartę Master, nadpisuje to z automatu całą inteligentną detekcję danego pomieszczenia. Pokój znika z grafu operacyjnego dla całego wydziału aż do momentu ponownego zwolnienia karty po wyjściu obsługi.

Podsumowując, nasz unikalny system podejmuje długą i solidną drogę programistyczną. Zaczynamy od hardware’owych detektorów pod sufitem ograniczających problematykę RODO (syntaktyka). Następnie zestawiamy

je z wejściami legitymacji i wyliczamy ułamek zajętości miejsc, ubezpieczając się na wypadek wejścia kogoś niejawnie (semantyka). Wrzucenie tego w końcową, wielostopniową listę statusów stanowi dowód na to, jak z tysiąca odczytów radiowych uzyskać prostą i użyteczną tablicę decyzji dla zabieganego studenta przed wykładem.

3.5 Ile faktycznie "wiedzy"daje system? (Entropia Shannona)

Ale ile tak naprawdę czystej „wiedzy” dajemy studentowi na tym ekranie? Żeby nie być gołosłownym, postanowiliśmy przeliczyć to korzystając z matematycznego aparatu teorii informacji. Zgodnie z koncepcją Shannona, wartość informacji to po prostu „element zaskoczenia”. Im rzadszy jest dany kolor kafelka na ekranie, tym bardziej redukuje on naszą niepewność i tym więcej „bitów informacji” ze sobą niesie.

Zebraliśmy próbne statystyki z naszego radaru z najbardziej obleganych godzin (10:00 - 14:00) dla testowej sali Jet Brains. Wyszło nam, że pełny, 5-stanowy model rozkłada się następująco:

- **Wolne / Dużo miejsc (Zielony):** 35% czasu ($p = 0.35$).
- **Umiarkowany ruch (Żółty):** 30% czasu ($p = 0.30$).
- **Prawie pełny (Pomarańczowy):** 20% czasu ($p = 0.20$).
- **Pełny (Czerwony):** 10% czasu ($p = 0.10$).
- **Sprzątanie (Szary):** 5% czasu ($p = 0.05$).

Teraz wystarczy wrzucić to do klasycznego wzoru na samoinformację: $I(x) = -\log_2(p(x))$.

Kolor na ekranie	**Prawdopodobieństwo**	**Ilość informacji [bit]**
Zielony (Wolne / Dużo miejsc)	0.35	~ 1.51
Żółty (Umiarkowany ruch)	0.30	~ 1.74
Pomarańczowy (Prawie pełny)	0.20	~ 2.32
Czerwony (Pełny)	0.10	~ 3.32
Szary (Sprzątanie)	0.05	~ 4.32

Tabela 1: Twarde wyliczenie bitów informacji dla naszych kafelków.

Jak na dłoni widać, że jak system wypluje szary kafelek „Sprzątanie”, to student dostaje gigantyczny strzał informacyjny (aż 4.32 bita zaskoczenia), bo to bardzo rzadka sytuacja. Z kolei zielony i żółty status pojawiają się częściej, więc niosą mniej informacji jednostkowej.

Mając te liczby, z łatwością policzyliśmy średnią niepewność (czyli słynną Entropię H) całego naszego wirtualnego pokoju:

$$H(X) = \sum p(x) \cdot I(x) = (0.35 \cdot 1.51) + (0.30 \cdot 1.74) + (0.20 \cdot 2.32) + (0.10 \cdot 3.32) + (0.05 \cdot 4.32) \approx 2.06\text{bita} \tag{1}$$

Maksymalna entropia dla układu 5-stanowego wynosi w teorii około $\log_2(5) \approx 2.32$ bita. Nasz wynik, czyli 2.06 bita na każde spojrzenie na ekran, to mocny dowód pragmatyczny. Pokazuje to czarno na białym, że nasza wizualizacja zdejmuje ze studentów konkretną porcję niewiadomych, optymalizując ich ruchy po wydziale.

3.6 Architektura przesyłu danych

Aby system tak płynnie przechodził od czujników do ostatecznej oceny zajętości na wyświetlaczach w holu, korzystamy ze świetnie zaplanowanej architektury technologicznej. Poniższy obraz przedstawia najważniejsze moduły tego układu:

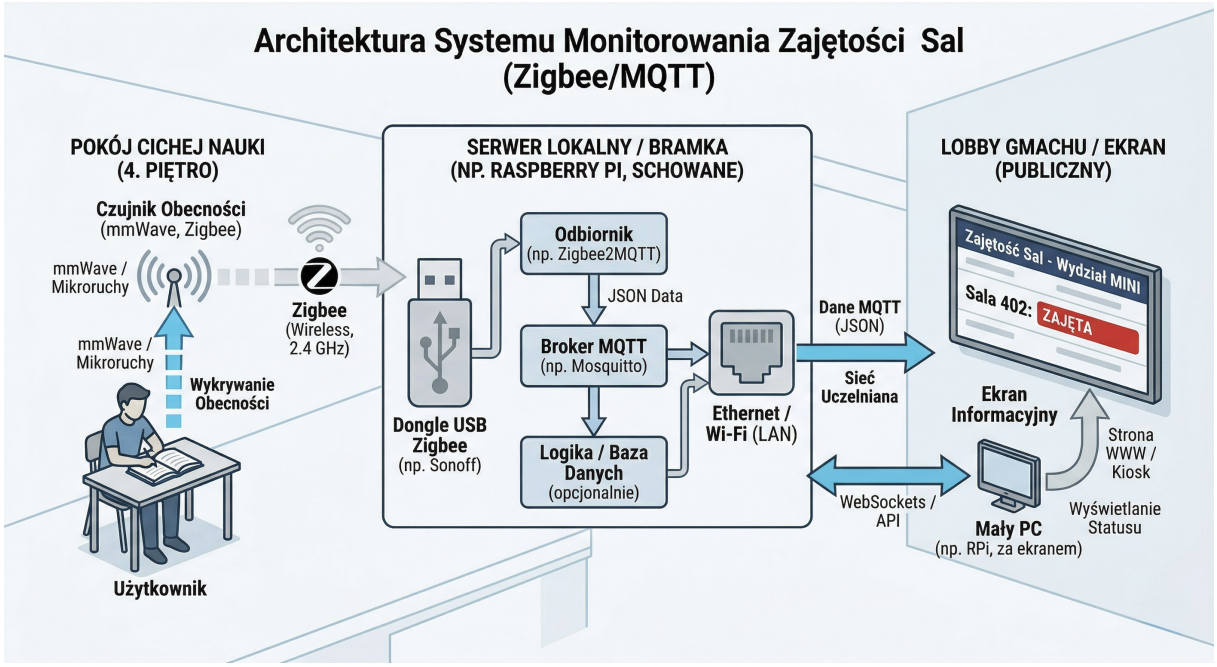

Rysunek 3: Architektura Systemu Monitorowania Zajętości Sal w technologii Zigbee i MQTT.

Działanie całości jest bardzo proste i można je opisać w zaledwie trzech krokach przepływu informacji:

- **1. Środowisko fizyczne (Pokój Nauki - lewa strona):** Czujnik (rozpoznający ruch fizyczny z radaru) wykrywa, że student siedzi przy biurku. Ponieważ używa niezwykle energooszczędnej technologii Zigbee, wysyła wynik detekcji w powietrze drogą bezprzewodową na częstotliwości 2.4 GHz.
- **2. Hub Główny (Serwer Ukryty - środek):** Gdzieś dalej w budynku schowany jest malutki mikrokomputer nadzorczy (np. tanie, małe Raspberry Pi). Posiada on wetknięty do gniazda "gwizdek"USB (dongle przypominający pendrive), który świetnie radzi sobie z przechwytywaniem tych sygnałów z powietrza. Kiedy komputer je wyłapie, specjalne programy narzędziowe (np. protokół MQTT) tłumaczą surowy szum antenowy na klasyczny, ludzki tekst komputerowy typu "stan: obecność"i wgrywają to do głównej, twardej sieci ethernetowej uczelni.
- **3. Klient Końcowy (Z publicznym ekranem - prawa strona):** Sam wielki telewizor w holu wyposażony jest po prostu w kolejny minikomputer stykający się ze stroną WWW. Ten komputer w holu nie przeprowadza detekcji ani żadnych skomplikowanych obliczeń radarów i anten – jest stacją wyjściową. Przez internet co chwilę komunikuje się dyskretnie z Serwerem Ukrytym i na podstawie gotowego już wyniku po prostu maluje duży pasujący kafelek statusu ("Sala: Zajęta") prosto w oczy mijających go potoków studentów.

Rozbicie fizyki na te trzy elementy sprzętowe mocno upraszcza pisanie każdej linijki kodu oraz pozwala np. zresetować duży ekran w holu bez przerywania analizy liczenia wejściówek do stref nauki.

3.7 Podsumowanie przepływu informacji w architekturze systemu

W celu ostatecznego uporządkowania przetwarzanych danych, poniższa tabela zestawia zaimplementowane w systemie warstwy informacji zgodnie z klasycznym podziałem badawczym:

Warstwa Informacji	Opis w systemie „MINI Info”	Wartość dla odbiorcy docelowego
Syntaktyczna	Surowe sygnały z czujników mmWave (radary) oraz logi RFID. Czyste wartości liczbowe (`int`) bez kontekstu przestrzennego.	Brak (czysty szum informacyjny, niezrozumiały dla studenta w holu).
Semantyczna	Kontekstualizacja danych przez algorytm. Powiązanie surowej liczby osób z maksymalną pojemnością konkretnej sali (np. 18/25 osób).	Średnia (wymaga od studenta analizy i znajomości pojemności danej sali).
Pragmatyczna	Gotowy, skwantyzowany komunikat decyzyjny wyświetlany na ekranie (np. status ŻÓŁTY – Umiarkowany ruch, lub rekomendacja innej sali).	Bardzo wysoka (użyteczna wiedza bezpośrednio redukująca „koszt dotarcia”).

Tabela 2: Zestawienie poziomów modelowania informacji w projektowanym systemie.

4 Analiza alternatywnych metod akwizycji i wybór technologii

4.1 Analiza alternatywnych metod akwizycji (State-of-the-art)

W procesie projektowania systemu dokonaliśmy przeglądu literatury oraz dostępnych metod rejestracji sygnałów, oceniając ich przydatność w kontekście określonego modelu użytkowego. Rozważaliśmy trzy główne podejścia do monitorowania zajętości stref na wydziale:

- **Metody wizyjne (Computer Vision):** Wykorzystanie kamer i algorytmów detekcji obiektów (np. YOLO) oferuje najwyższą informatywność sygnału, pozwalając na precyzyjną ocenę jakości i specyfiki danych. Jednakże, z punktu widzenia pragmatyki, rozwiązanie

to zostało odrzucone ze względu na restrykcyjne normy prywatności (RODO) oraz ogromną nadmiarowość danych, która wymagałaby skomplikowanych metod kompresji obrazu i dużej przepustowości kanału informacyjnego.

- **Sensory pasywnej podczerwieni (PIR):** Jest to rozwiązanie o najniższym koszcie i najprostszej binarnej reprezentacji kodów. Niestety, sygnał z czujników PIR jest wysoce zaszumiony i obarczony artefaktami – czujnik przestaje dostarczać informacji, gdy obiekt pozostaje w bezruchu. Z perspektywy teorii informacji, wiarygodność i reprezentatywność takich danych w pokoju cichej nauki byłaby niewystarczająca do poprawnej rekonstrukcji stanu świata rzeczywistego.

- **Analiza pośrednia (sensory CO2 / Wi-Fi):** Rozważaliśmy monitorowanie parametrów środowiskowych jako pośrednich wskaźników obecności ludzi. Metody te charakteryzują się jednak bardzo dużymi opóźnieniami w dostarczaniu informacji, co narusza kryterium aktualności sygnału w modelu czasu rzeczywistego.

4.2 Uzasadnienie wyboru technologii (Synteza wniosków)

Ostateczny wybór radarów milimetrowych (mmWave) wspieranych przez system RFID wynika z chęci optymalizacji relacji między jakością informacji a ograniczeniami systemu. Radar mmWave dostarcza nam sygnał o średniej złożoności, który jest znacznie bardziej odporny na szumy niż PIR, a jednocześnie nie narusza prywatności tak jak systemy wideo.

Zdecydowaliśmy się na tę technologię, ponieważ pozwala ona na:

1. **Redukcję nadmiarowości na poziomie źródła:** Otrzymujemy gotową informację o liczbie osób (typ `integer`), co eliminuje potrzebę przesyłania i przetwarzania złożonych strumieni multimedialnych.

2. **Wysoką wiarygodność semantyczną:** Fuzja danych z radaru (skanowanie ciągłe) i czytnika RFID (zdarzenia progowe) pozwala na skuteczną weryfikację zgromadzonych zasobów i rozwiązanie problemu odwrotnego przy ograniczonej liczbie pomiarów.

3. **Efektywność pragmatyczną:** Wykorzystanie standardu ZigBee i protokołu MQTT zapewnia minimalny koszt energetyczny i transmisyjny, co w teorii informacji przekłada się na optymalne zarządzanie archiwum danych przy zachowaniu wysokiej użyteczności dla studenta.

W ten sposób dokonany przez nas wybór stanowi kompromis pomiędzy technicznymi uwarunkowaniami pomiaru a realnymi potrzebami użytkowników, zapewniając dostarczanie sygnałów o najwyższej informatywności przy minimalnych zniekształceniach.

4.3 Implikacje pragmatyczne dla użytkownika końcowego

Z perspektywy studenta kluczowe jest to, że warstwa semantyczna nie kończy się na surowym odczycie liczby osób, lecz zostaje przekształcona w prosty interfejs decyzyjny na ekranach w lobby. Zamiast analizy pojedynczych pomiarów, odbiorca otrzymuje intuicyjną paletę pięciu stanów (od zielonego przez żółty i pomarańczowy po czerwony oraz szary tryb techniczny), co skraca czas interpretacji komunikatu do pojedynczego spojrzenia.

W ujęciu teorii informacji taki model prezentacji jest również ilościowo uzasadniony. Zgodnie z wcześniejszym wyliczeniem entropii Shannona, system dostarcza średnio około 2.06 bita informacji na każdą obserwację tablicy, co przekłada się na realną redukcję niepewności użytkownika. W efekcie student szybciej podejmuje decyzję o wyborze strefy, a liczba „pustych przebiegów” między kondygnacjami zostaje zauważalnie ograniczona.

5 Metryki efektywności i optymalizacja przesyłu (Kompresja i Jakość)

Każdy system informatyczny dostarczający użytkownikowi końcowemu wartościowej informacji w czasie rzeczywistym musi mierzyć się z fundamentalnym pytaniem inżynierskim: ile danych naprawdę potrzebujemy przesłać, żeby odpowiedź była użyteczna? W naszym przypadku pytanie to przyjmuje bardzo konkretną formę. Student stojący w holu Wydziału Matematyki i Nauk Informacyjnych chce wiedzieć jedną rzecz: czy warto iść na górę do Pokoju Cichej Nauki, strefy JetBrains, czy może lepiej zająć kanapę na korytarzu. Droga do uzyskania tej odpowiedzi może różnić się o kilka rzędów wielkości pod względem ilości przesyłanych danych, złożoności obliczeniowej i ryzyka prawnego.

5.1 Porównanie podejść: kamery kontra czujniki obecności

Zanim przejdziemy do omawiania metryk i optymalizacji w kontekście naszego systemu, warto osadzić nasze decyzje projektowe na tle alternatyw-

nego podejścia opartego na kamerach wideo. Analiza porównawcza pozwala bowiem najlepiej uzasadnić wybory poczynione na etapie projektowania architektury.

Systemy oparte na kamerach charakteryzują się bardzo wysoką wymaganą przepustowością sieci. Pojedyncza kamera 1080p przesyła surowy strumień rzędu 3–6 Gb/s przed kompresją. Nawet po zastosowaniu kodowania H.264 do poziomu typowego dla systemów nadzoru (2–4 Mb/s na kamerę), sieć wydziałowa przy założeniu 12 kamer musiałaby obsługiwać ciągły ruch rzędu 24–48 Mb/s. To obciążenie generuje poważne koszty infrastrukturalne i wymaga dedykowanego serwera do przetwarzania obrazu w czasie rzeczywistym.

Co jednak ważniejsze – dane z kamer stanowią z definicji dane osobowe w rozumieniu RODO. Obraz twarzy czy sylwetki pozwala na identyfikację konkretnej osoby fizycznej. Nawet systemy stosujące anonimizację w czasie rzeczywistym przez ułamek sekundy przetwarzają pełny obraz, co technicznie oznacza, że dane osobowe istnieją w pamięci systemu. Wdrożenie takiego rozwiązania na uczelni wymagałoby przeprowadzenia oceny skutków dla ochrony danych (DPIA) oraz konsultacji z uczelnianym inspektorem ochrony danych. Co więcej, samo poinformowanie użytkowników przestrzeni o monitoringu wizyjnym zmieniałoby charakter tych stref jako miejsc spokojnej nauki.

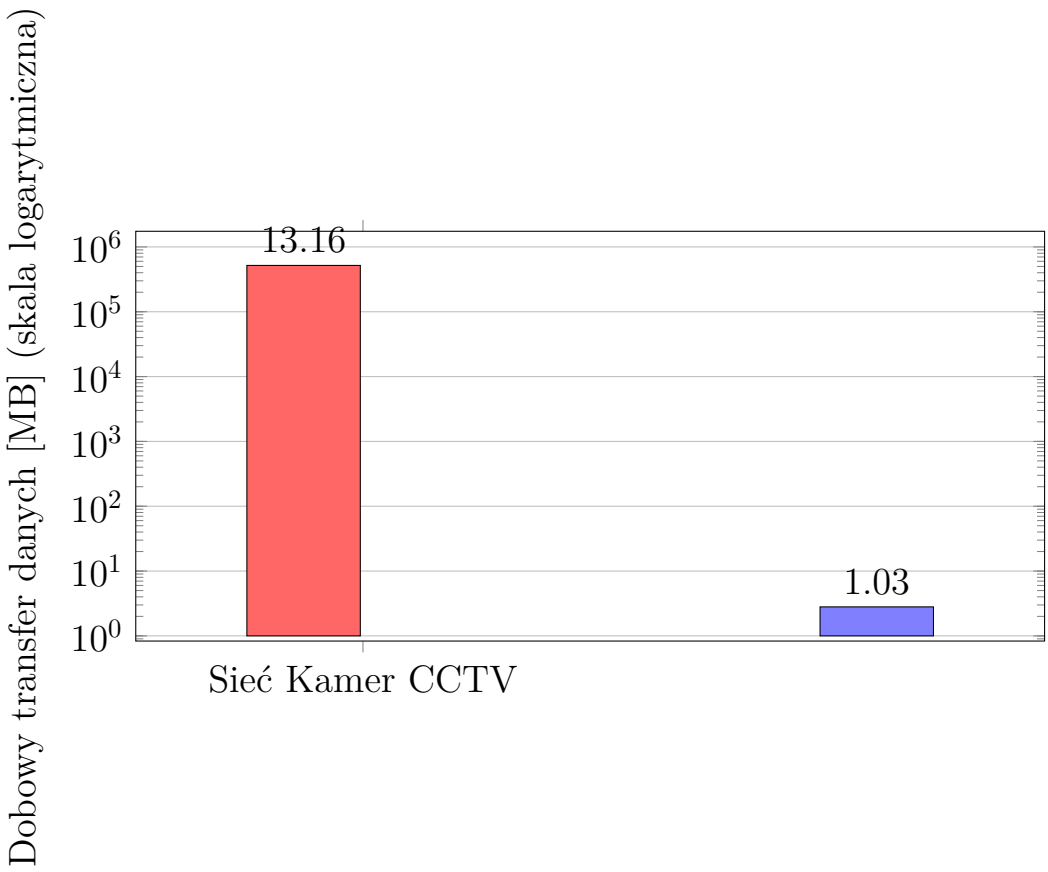

Rysunek 4: Porównanie dobowego obciążenia sieci wydziałowej dla 12 węzłów obserwacyjnych. Zastosowanie sensorów milimetrowych pozwala na redukcję przesyłanych danych o ponad pięć rzędów wielkości.

Nasz system oparty na czujnikach milimetrowych oraz czytnikach legitymacji całkowicie omija ten problem – co zostało szczegółowo omówione w rozdziale dotyczącym poziomu syntaktycznego. Z perspektywy niniejszego rozdziału kluczowe jest natomiast to, co ta decyzja oznacza dla ilości przesyłanych danych i wymagań obliczeniowych. Pojedynczy odczyt czujnika mmWave to komunikat nieprzekraczający kilkudziesięciu bajtów. Przy odpytywaniu co 30 sekund, sumaryczny ruch generowany przez 8 czujników wynosi mniej niż 2 KB/min – w skali doby około 2,8 MB. Jest to wartość o cztery do pięciu rzędów wielkości mniejsza niż w przypadku systemu kamerowego, co przekłada się na znikome wymagania infrastrukturalne i brak potrzeby stosowania jakiejkolwiek kompresji strumieniowej.

5.2 Granularność danych wyjściowych i kryteria jakości informacji

Przyjęta architektura czujnikowa narzuca konkretny kształt danych, jakie system jest w stanie dostarczyć, i warto ten kształt precyzyjnie zdefiniować

jako metrykę jakości informacji.

Naszym podstawowym wyjściem jest liczba całkowita reprezentująca liczbę osób aktualnie przebywających w danej strefie. Jest to celowo surowa, liczbowa wartość – nie uproszczony stan semantyczny. Świadomie rezygnujemy z dostarczania jedynie etykiety „wolne/zajęte”, ponieważ student podejmując decyzję o przemieszczeniu się na wyższe piętro ocenia sytuację bardziej subtelnie. Informacja „4/6 miejsc zajętych” jest znacznie wartościowsza decyzyjnie niż samo „częściowo zajęte” – pozwala ocenić, czy znajdzie się miejsce przy konkretnym biurku, czy warto w ogóle podejmować wędrówkę. Liczba osób stanowi więc metrykę pierwszego rzędu, z której interfejs użytkownika może samodzielnie wyprowadzić dowolną reprezentację wizualną – ułamek zajętości, pasek postępu, kolor kafelka.

Kluczowym kryterium jakości w naszym systemie jest aktualność informacji, czyli maksymalne dopuszczalne opóźnienie między zmianą stanu fizycznego pomieszczenia a aktualizacją danych na ekranie. Dla naszego zastosowania przyjmujemy jako akceptowalne opóźnienie rzędu jednej minuty – decyzja studenta o przemieszczeniu się nie wymaga danych aktualizowanych co sekundę, a raczej co kilkanaście do kilkudziesięciu sekund. Drugim kryterium jest spójność danych między dwoma źródłami – czujnikiem mmWave i czytnikiem RFID. Jak opisano w rozdziale dotyczącym semantyki, algorytm wybiera zawsze wyższą z dwóch wartości, traktując ją jako bezpieczniejsze oszacowanie. Z punktu widzenia metrycznego oznacza to, że system jest zaprojektowany tak, aby raczej zawyżać niż zaniżać obłożenie – co chroni studenta przed niepotrzebną wędrówką do faktycznie zajętej sali.

Trzecim istotnym kryterium jakości jest kompletność pokrycia stref. System musi dostarczać dane dla wszystkich monitorowanych lokalizacji jednocześnie, bez „ślepych plam”, które zmuszałyby studenta do samodzielnego sprawdzenia danego miejsca. W praktyce oznacza to wymaganie na dostępność każdego węzła sieci czujnikowej na poziomie bliskim 100% w godzinach funkcjonowania wydziału. Sieć ZigBee w topologii mesh częściowo adresuje ten problem poprzez redundancję ścieżek komunikacyjnych – awaria pojedynczego węzła nie odcina pozostałych czujników od bramki.

5.3 Forma przesyłu danych i ich analiza

Dane z czujników są zbierane przez bramkę podłączoną do sieci LAN wydziału i przesyłane do serwera protokołem MQTT. Każdy komunikat ma rozmiar nieprzekraczający 64 bajtów i zawiera identyfikator czujnika, znacznik czasu oraz aktualną liczbę wykrytych osób. Protokół MQTT jest tu wyborem nieprzypadkowym – jego architektura oparta na modelu publikacja-

subskrypcja (publish-subscribe) pozwala na elastyczne dodawanie nowych czujników do sieci bez modyfikacji istniejącej infrastruktury serwerowej. Nowy czujnik po prostu zaczyna publikować dane na dedykowanym kanale tematycznym (topic), a serwer automatycznie go subskrybuje.

Na serwerze dane są agregowane i przechowywane w bazie danych szeregów czasowych. Dla celów bieżącego wyświetlania wystarczający jest ostatni odczyt z każdego czujnika. Dla celów analitycznych – na przykład wyznaczania wzorców obłożenia w ciągu dnia lub tygodnia, co może być przydatne przy planowaniu godzin dostępności stref – przechowujemy dane zagregowane do rozdzielczości 5-minutowej. Dane historyczne w rozdzielczości godzinowej pozwalają z kolei na analizę długoterminowych trendów, np. porównanie obłożenia strefy JetBrains w tygodniu sesyjnym versus normalnym tygodniu zajęć.

Surowe dane z czujników są przechowywane przez 48 godzin w celu umożliwienia debugowania, po czym automatycznie usuwane. Polityka ta jest zgodna z zasadą minimalizacji danych wynikającą z RODO. Szacowane łączne zapotrzebowanie na przestrzeń dyskową dla całej sieci czujników wynosi około 50 MB miesięcznie – wartość pomijalna z punktu widzenia infrastruktury serwerowej uczelni.

Wynikowy stan każdej strefy eksponowany jest przez REST API, z którego korzysta interfejs wyświetlany na ekranach w holu. Całkowite opóźnienie systemu – od zmiany stanu fizycznego do aktualizacji ekranu – wynosi w normalnych warunkach poniżej 45 sekund i wynika głównie z przyjętego interwału odpytywania czujników oraz czasu propagacji danych przez stos MQTT. Wartość ta spełnia z dużym zapasem przyjęte kryterium jakości dotyczące aktualności informacji.

Etap w systemie	**Format danych**	**Działanie w kontekście PTI**	**Częstotliwość / Interwał**
1. Akwizycja (Sensory mmWave)	Sygnał ciągły (fala radiowa)	Ekstrakcja cech i ekstremalna kompresja wymiarowości zjawiska fizycznego.	Czas rzeczywisty
2. Transmisja (Protokół MQTT)	Dyskretny ładunek JSON (< 64 bajtów)	Redukcja nadmiarowości kanału transmisyjnego (model subskrypcji).	Co 45-60 sekund
3. Agregacja (Baza Szeregów)	Wartość uśredniona (`float`)	Downsampling w dziedzinie czasu (potencjalny aliasing krótkich zdarzeń).	Okno 5-minutowe
4. Prezentacja (REST API $\rightarrow$ Ekran)	Metadane stanu (`np. "status": "RED"`)	Ostateczna kwantyzacja użyteczna dla celów decyzyjnych odbiorcy (Pragmatyka).	Na żądanie klienta (< 200 ms)

Tabela 3: Cykl życia informacji w systemie MINI Info – od zjawiska ciągłego po użyteczny sygnał decyzyjny.